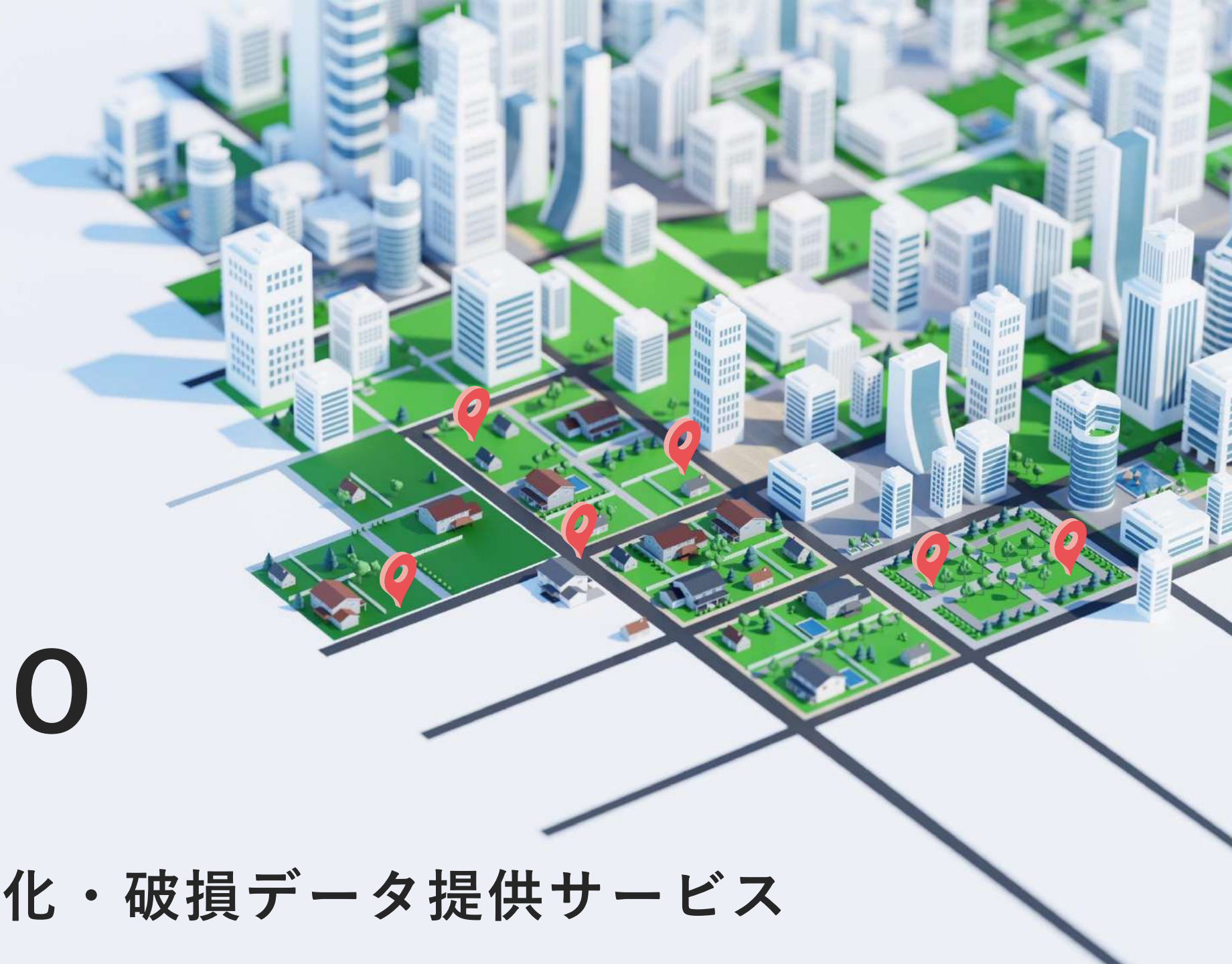

HOHOHO

交通安全施設
リアルタイム劣化・破損データ提供サービス

壊れてから直す、から
壊れにくく育てる、へ。

HOHOHOは、歩行によって取得した
リアルタイムの現場データをもとに、
交通安全施設の劣化・破損状況を可視化します。

取得データを各業界や行政に共有することで、
より安全で持続可能な街づくりに向けた
意思決定を支援します。

歩行という低コスト手段を
インフラ管理の補完リソースとして活用



歩くと見える、街に潜むリスク

Awara Kaido

注

サービス提供の背景

街を歩くと「車では見逃されがちなリスク」が数多く潜んでいることに気が付きます
例えば側溝溝が破損していたり、ガードレールに穴が空いていたり。
そこで本サービスでは各企業と連携し、予防保全に貢献できないかと考えたのがきっかけです

①あるく → ②きがつく → ③みちがえる

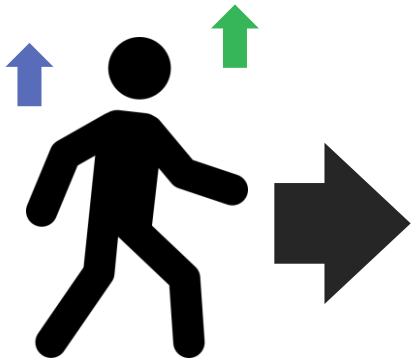

歩くことによる健康効果
メンタルヘルス

側溝溝の破損

標識の折れ曲がり

ガードレールの穴

防護柵の曲がり

共有

行政

各企業

老若男女がより安心して歩けるまちづくりへの貢献

文字通り、一歩一歩が街の安全を守る行動につながる!!

運用テストで見えた「想定以上の未把握リスク」

実際に福井市管理課さまとお打ち合わせを行った後、運用テストを実施しました。
結果、既存体制では拾われていなかった“初期リスク”が短期間で多数確認される結果となりました。

対象：福井市二の宮周辺
期間：1ヶ月
調査者：1名（1日1時間）
確認件数：約367件

参考データ
行政修繕：約1,600件／年
市民通報（LINE）：約100件／年

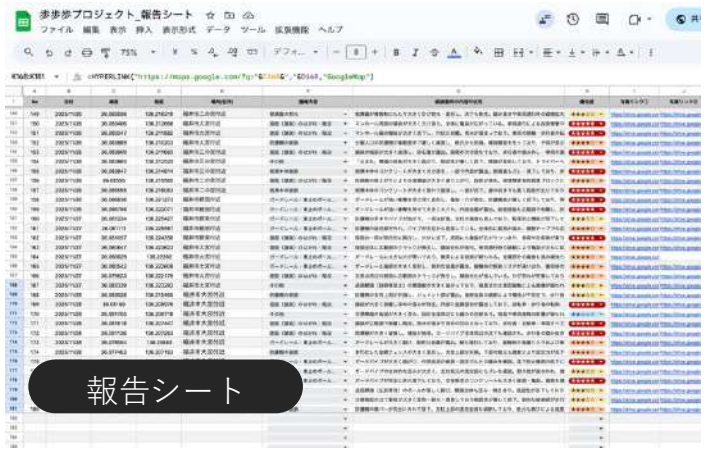

報告シート

ヒートマップ

現地印刷用シート

集計シート

一部エリアでのデータとなりますが
エリア観点で見ても人口密度の高いエリアでの損傷が目立つ結果となりました

歩歩歩プロジェクト_報告シート

ファイル　編集　表示　挿入　表示形式　データ　ツール　拡張機能　ヘルプ

D357　136.238264

	A	B	C	D	E	F	G	H	I	J	K	L
1	No	日付	緯度	経度	地区	管轄	通報内容	破損箇所の内容や状況	損傷レベル	損傷	人流	合計値
111	110	2025/11/22	36.090126	136.205654	新田塚一丁目	えちぜん鉄道	防護柵の破損	コンクリート支柱が大きく傾き、鉄製の横桟も著しく腐食している。固定	★★★★★	5	5	25
182	181	2025/11/29	36.074049	136.21186	乾徳一丁目	えちぜん鉄道	防護柵の破損	コンクリート柵が複数箇所で折損・脱落。踏切横で人が転落する危険が高	★★★★★	5	4	20
183	182	2025/11/29	36.076807	136.207236	文京四丁目	えちぜん鉄道	防護柵の破損	コンクリート柵が倒壊し蔦で覆われているため視認性が低い。根元も腐食	★★★★☆	4	5	20
184	183	2025/11/29	36.077248	136.207024	文京四丁目	えちぜん鉄道	防護柵の破損	コンクリート柵が斜めに傾き、梁の破損と金具の腐食が進行。歩道側に倒	★★★★★	5	5	25
231	230	2025/12/1	36.076949	136.227719	町屋三丁目	えちぜん鉄道	防護柵の破損	コンクリート柵が完全に折損し、鉄筋が露出した状態で垂れ下がっている	★★★★★	5	5	25
232	231	2025/12/1	36.076419	136.226574	町屋三丁目	えちぜん鉄道	防護柵の破損	線路沿いのコンクリート製フェンスが広範囲で破断し、上部の梁が完全に	★★★★★	5	5	25
261	260	2025/12/4	36.07512	136.216808	田原一丁目	えちぜん鉄道	防護柵の破損	木製防護柵が複数箇所で折損し、支柱ごと破断している箇所も確認される	★★★★★	5	5	25
267	266	2025/12/5	36.076908	136.227802	町屋三丁目	えちぜん鉄道	防護柵の破損	コンクリート製の横桟が折損し、一部が地面に落下。支柱接合部も腐食・	★★★★★	5	5	25
268	267	2025/12/5	36.076745	136.226744	町屋三丁目	えちぜん鉄道	防護柵の破損	桟が大きくずれ、接合金具が腐食し固定力を失っている。支柱との結合が	★★★★★	5	5	25
269	268	2025/12/5	36.076411	136.22675	町屋三丁目	えちぜん鉄道	防護柵の破損	横桟の破断に加え、支柱の腐食が著しく、複数箇所で金具が脱落。全体が	★★★★★	5	5	25
355	354	2025/12/12	36.073492	136.237174	志比口三丁目	えちぜん鉄道	防護柵の破損	コンクリート製の防護柵が複数箇所で折損・脱落しており、鉄筋が露出。	★★★★★	5	5	25
356	355	2025/12/12	36.07365	136.237813	西開発一丁目	えちぜん鉄道	防護柵の破損	コンクリート防護柵が複数箇所で折損・大きく傾き、支柱の脱落や鉄筋露	★★★★★	5	4	20
357	356	2025/12/12	36.073837	136.238264	西開発一丁目	えちぜん鉄道	防護柵の破損	同上。極めて広範囲に同じような状況が続いている	★★★★★	5	4	20

修繕・点検業務を軽くする「歩行者目線の劣化把握データ」

① 修繕計画に使える「現状把握データ」

駅・踏切・沿線における歩行者動線上の劣化・破損状況の把握、どこがどう壊れているか
どの程度進行しているか「次にどこを直すか」を考える材料

② パトロール頻度を見直すための材料

定期パトロールでは拾いきれない箇所を第三者視点で継続観測。問題が出やすい場所、変化が起きにくい場所「ここは頻度を落としていい」「ここは重点的に見るべき」の判断材料

③ 点検・修繕判断の前工程を外出しできる

社内で行っている「まず現地を見に行く」を減らす
現地確認・写真取得・状況整理。その“最初の一歩”をHOHOHOが担う

調査手段別の特性比較

調査手段	調査範囲	
車両調査	広範囲・顕在化リスク向き	両者は競合ではなく補完関係
歩行調査	狭域・初期リスク・生活目線の変状向き	

車と歩行の“発見特性の違い”

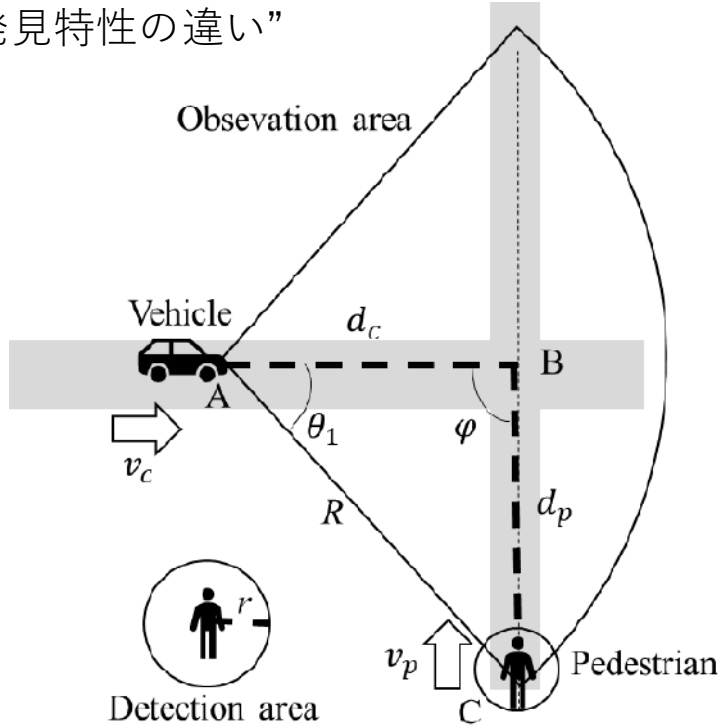

子ども“通学路の利用者”

・身体が未成熟なため街の危険の影響を受けやすい
・ほんの数センチの段差でも転倒リスク大

車を卒業した高齢者“徒歩・自転車が中心”

・道路インフラの“影響を最も受けやすい”層
・小さな段差・側溝の隙間・傾き・滑りやすさが
　重大事故につながる（行政が最も守るべき対象）
・免許返納したあとも外出を安全に楽しんでほしい

歩歩歩プロジェクト_報告シート

ファイル　編集　表示　挿入　表示形式　データ　ツール　拡張機能　ヘルプ

メニュー　100%　¥　%　.0　.00　123　デフォ…　8

HOHOHOが提供するデータ

H:N　破損箇所の内容や状況

	A	B	C	D	E	F	G	H	I	J	K	L	M
1	No	日付	緯度	経度	地区	管轄	通報内容	破損箇所の内容や状況	損傷レベル	損傷	人流	合計値	近隣地形リ
2	001	2025/11/12	36.08522	136.224342	二の宮二丁目	県道	その他	街路樹の根が成長し石垣ブロックが持ち上がって破損。歩道縁石のズレあ	★★★★☆	4	5	20	⑤ 住宅地・
3	002	2025/11/12	36.064561	136.21771	順化一丁目	県道	側溝蓋の割れ	側溝蓋のズレと舗装ひび割れ。歩道境界の沈下が進行し危険。	★★★★★	5	5	25	⑤ 住宅地・
4	003	2025/11/12	36.064792	136.217525	順化一丁目	県道	その他	石垣ブロックの一部が崩落。内部の土が流出しており、歩道側への崩れ拡	★★★★☆	4	5	20	② 橋・法面・盛土
5	004	2025/11/12	36.065454	136.217764	順化一丁目	県道	側溝本体破損	側溝周辺の石ブロックが大きく破損し、根上がりによるズレも顕著。段差	★★★★★	5	5	25	
6	005	2025/11/12	36.065762	136.217714	順化一丁目	県道	側溝蓋の割れ	側溝蓋が変形・沈下し、周囲の舗装も亀裂。歩行時のつまずきリスクあり	★★★★☆	4	5	20	
7	006	2025/11/12	36.066686	136.217937	大手三丁目	県道	その他	街路樹の根上がりにより縁石が浮き、側溝がずれている。歩道タイルに段	★★★★☆	4	7	28	
8	007	2025/11/12	36.066765	136.218033	大手三丁目	県道	路面（舗装）のはがれ・…	点字ブロック周辺のタイルが複数割れ、沈下と隆起が混在。車椅子・高齢	★★★★★	5	7	35	
9	008	2025/11/12	36.071693	136.218376	田原一丁目	県道	路面（舗装）のはがれ・…	歩道タイルが剥離し、アスファルト補修跡が不均一。段差と隙間がありつ	★★★★☆	4	5	20	
10	009	2025/11/12	36.071731	136.218357	田原一丁目	県道	路面（舗装）のはがれ・…	黒タイルの一部が浮き上がり、端部が割れ。視覚障害者誘導ブロックとの	★★★☆☆	3	5	15	
11	010	2025/11/12	36.084385	136.222431	二の宮二丁目	中2-63	路面（舗装）のはがれ・…	アスファルト舗装に大きなひび割れと段差あり。自転車・歩行者がつまず	★★★★☆	4	5	20	
12	011	2025/11/12	36.08522	136.224342	二の宮二丁目	市管理道路	側溝本体破損	側溝端部のコンクリートが大きく割れて欠落。通水口の破損により歩行時	★★★★★	5	5	25	
13	012	2025/11/16	36.081021	136.225803	幾久町	警察	その他	駐停車禁止標識が大きく曲がっており、表示面の一部が剥離。視認性が大	★★★☆☆	3	2	6	
14	013	2025/11/16	36.080784	136.225821	幾久町	警察	その他	進行方向指定（左折・直進）の標識下部にある大型車用補助標識が大きく	★★★☆☆	3	2	6	
15	014	2025/11/16	36.077873	136.225372	町屋三丁目	東環状線	その他	東環状線」の案内標識が大きく曲がり傾いている。案内方向が読み取りに	★★☆☆☆	2	5	10	
16	015	2025/11/16	36.075227	136.221772	文京一丁目	中1-469	防護柵の破損	ガードレールが大きく凹み、鋼材が裂けている。衝突痕があり、防護機能	★★★★★	5	5	25	
17	016	2025/11/16	36.075124	136.219686	松本四丁目	中1-469	防護柵の破損	鉄パイプの防護柵が全体的に腐食し、複数箇所で曲がり・脱落。線路との	★★★★☆	4	5	20	
18	017	2025/11/17	36.086116	136.227208	二の宮一丁目	警察	その他	道路標識（左折専用）の上部が大きく曲がり変形。支持部の腐食または強	★★★★☆	4	5	20	
19	018	2025/11/17	36.085969	136.22734	二の宮一丁目	警察	その他	左折指示標識および下部の「7-9」補助標識が大きく変形。衝撃痕があり補	★★★★☆	4	5	20	
20	019	2025/11/17	36.087051	136.228215	二の宮一丁目	警察	その他	「止まれ（STOP）」標識が大きく割れて反り返り、板面が湾曲。視認性が	★★★★★	5	5	25	
21	020	2025/11/17	36.086957	136.229051	二の宮一丁目	警察	その他	「駐停車禁止」標識の塗膜が広範囲に剥離し、色あせと腐食が進行。視認	★★★☆☆	3	5	15	
22	021	2025/11/17	36.086936	136.229276	二の宮一丁目	警察	その他	「駐停車禁止」標識に大きな割れと反りが発生。板面の破損により視認性	★★★★☆	4	5	20	
23	022	2025/11/17	36.087699	136.229626	二の宮一丁目	中2-45	ガードレール・車止めポ…	ガードレール全体に著しい腐食、レール変形、端部の大きな損傷を確認。	★★★★★	5	5	25	
24	023	2025/11/17	36.092104	136.229732	高木二丁目	北2-170	路面（舗装）のはがれ・…	道路舗装に多数のひび割れ（クラック）を確認。老朽化が進行しており、	★★★★☆	4	5	20	
25	024	2025/11/17	36.099764	136.226838	舟橋一丁目	県道	その他	橋の親柱コンクリートが大きく欠け落ち、内部が露出。構造劣化が進んで	★★★★☆	4	2	8	
26	025	2025/11/17	36.102601	136.225854	稲多元町	北1-189	その他	道路端の反射ポールが大きく傾斜し固定不良。夜間の視認性低下や接触事	★★★☆☆	3	2	6	
27	026	2025/11/17	36.098263	136.227095	舟橋一丁目	北2-1	防護柵の破損	側溝沿いガードレールが大きく曲がり、固定部も破損。歩行者の転落防止	★★★★☆	4	2	8	
28	027	2025/11/17	36.093638	136.228068	高木二丁目	警察	その他	「止まれ」標識が大きく湾曲し視認性低下。交通安全上の重要標識であり	★★★★☆	4	5	20	
29	028	2025/11/17	36.093616	136.227903	高木二丁目	警察	その他	「止まれ」標識が側方へ反り返り、取付部も変形。視認性が低下し事故リ	★★★★☆	4	5	20	
30	029	2025/11/17	36.093675	136.227928	高木二丁目	警察	その他	速度標識・駐車禁止標識の板面がひび割れ・湾曲し劣化。視認性確保のた	★★★☆☆	3	5	15	
31	030	2025/11/17	36.089619	136.228366	二の宮一丁目	県道	ガードレール・車止めポ…	ガードレール支柱の頭部キャップ欠損および固定金具破損。強度が低下し	★★★★☆	4	5	20	

対象No： 099　**日付：** 2025/11/21
緯度： 36.092380　**経度：** 136.227271

場所（住所）： 高木二丁目　**優先度：**
管理区分： 中2-413
通報内容： ガードレール・車止めポールの破損
破損箇所の状況： ガードレールが大きく湾曲・変形しており、支柱も著しく腐食。車両衝突の痕跡があり、強度が低下していて非常に危険な状態。早急な点検・交換が必要と思われる。

現場写真：

PDFのみまとめてお渡しすることも可能

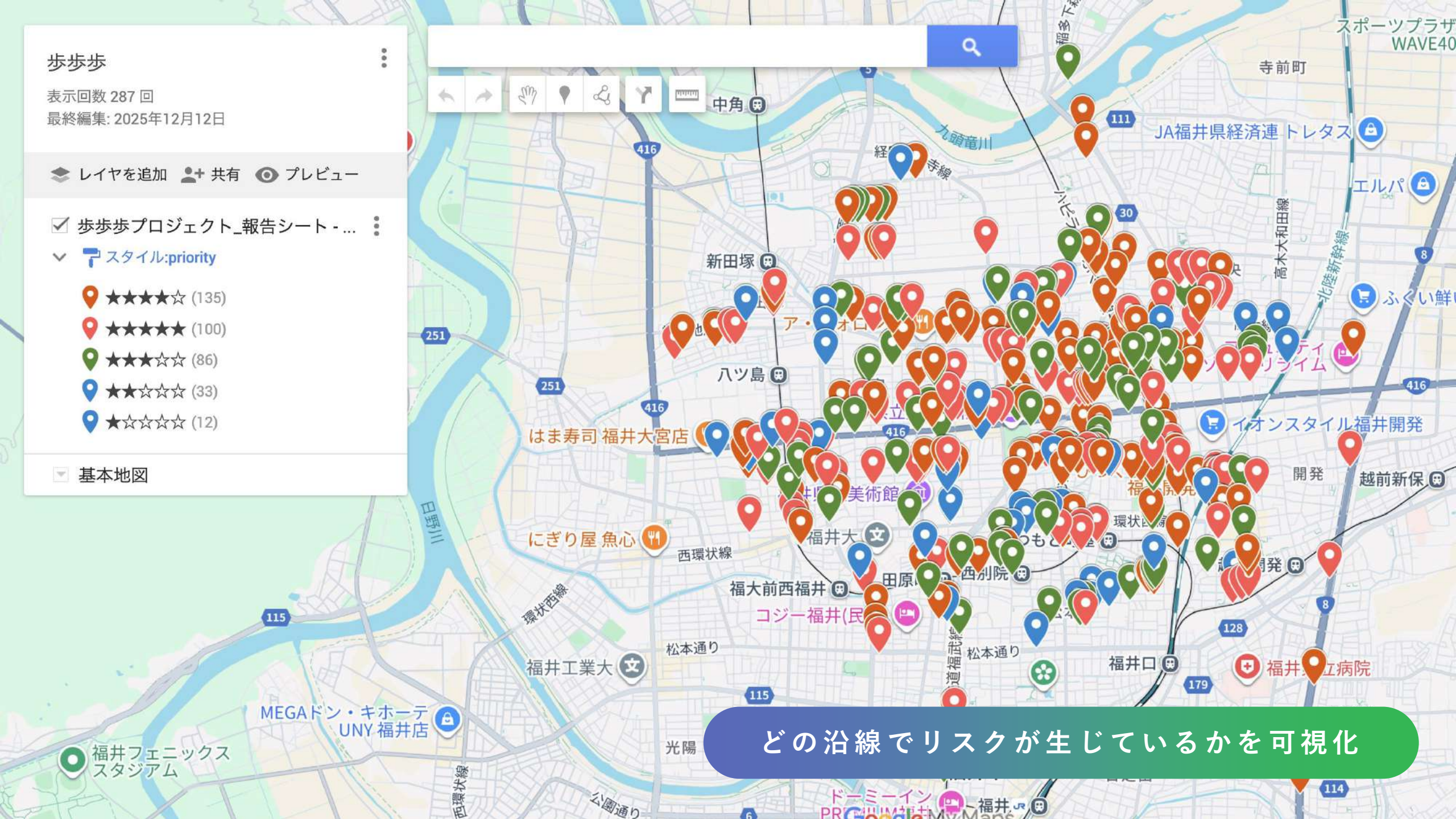
歩歩歩
表示回数 287 回
最終編集: 2025年12月12日
レイヤを追加
共有
プレビュー
歩歩歩プロジェクト_報告シート - ...
スタイル:priority
★★★★☆ (135)
★★★★★ (100)
★★★☆☆ (86)
★★☆☆☆ (33)
★☆☆☆☆ (12)
基本地図
中角
新田塚
八ツ島
はま寿司 福井大宮店
にぎり屋 魚心
福大前西福井
コジー福井(民
福井大
福井工業大
福井口
JA福井県経済連 トレタス
エルパ
ふくい鮮
イオンスタイル福井開発
越前新保
寺前町
九頭竜川
日野川
西環状線
環状西線
松本通り
MEGAドン・キホーテ UNY 福井店
福井フェニックス スタジアム
光陽
どの沿線でリスクが生じているかを可視化

046A.JPG

046B.JPG

046S.PNG

047A.JPG

047B.JPG

047S.PNG

048A.JPG

048B.JPG

048S.PNG

049A.JPG

049B.JPG

049S.PNG

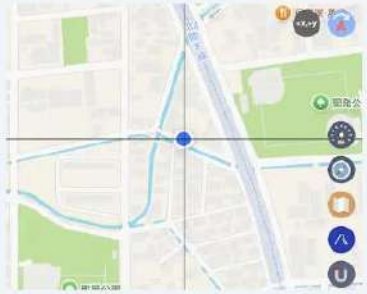

050A.JPG

050B.JPG

050S.PNG

051A.JPG

051B.JPG

051S.PNG

HOHOHOのデータは「現場で何が起きているか」をそのまま業務判断に使える形で提供します。

想定価格と提供イメージ｜現地一次情報

含まれる業務

歩行による現地確認
写真・位置・状況の取得
定期的な更新

含まれないこと

個別現地対応
追加調査
緊急対応

価格感（目安）

月額 5万円/月
年額契約なら 50万円/年

歩歩歩プロジェクト_報告シート

ファイル　編集　表示　挿入　表示形式　データ　ツール　拡張機能　ヘルプ

U16

No	日付	緯度	経度	地区	管轄	通報内容	写真リンク①	写真リンク②	地図リンク
001	2025/11/12	36.08522	136.224342	二の宮二丁目	県道	その他	https://drive.google.cor	https://drive.google.cor	GoogleMap
002	2025/11/12	36.064561	136.21771	順化一丁目	県道	側溝蓋の割れ	https://drive.google.cor		GoogleMap
003	2025/11/12	36.064792	136.217525	順化一丁目	県道	その他	https://drive.google.cor		GoogleMap
004	2025/11/12	36.065454	136.217764	順化一丁目	県道	側溝本体破損	https://drive.google.cor		GoogleMap
005	2025/11/12	36.065762	136.217714	順化一丁目	県道	側溝蓋の割れ	https://drive.google.cor		GoogleMap
006	2025/11/12	36.066686	136.217937	大手三丁目	県道	その他	https://drive.google.cor		GoogleMap
007	2025/11/12	36.066765	136.218033	大手三丁目	県道	路面（舗装）のはがれ・...	https://drive.google.cor		GoogleMap
008	2025/11/12	36.071693	136.218376	田原一丁目	県道	路面（舗装）のはがれ・...	https://drive.google.cor		GoogleMap
009	2025/11/12	36.071731	136.218357	田原一丁目	県道	路面（舗装）のはがれ・...	https://drive.google.cor		GoogleMap
010	2025/11/12	36.084385	136.222431	二の宮二丁目	中2-63	路面（舗装）のはがれ・...	https://drive.google.cor		GoogleMap
011	2025/11/12	36.08522	136.224342	二の宮二丁目	市管理道路	側溝本体破損	https://drive.google.cor		GoogleMap
012	2025/11/16	36.081021	136.225803	幾久町	警察	その他	https://drive.google.cor	https://drive.google.cor	GoogleMap
013	2025/11/16	36.080784	136.225821	幾久町	警察	その他	https://drive.google.cor	https://drive.google.cor	GoogleMap
014	2025/11/16	36.077873	136.225372	町屋三丁目	東環状線	その他	https://drive.google.cor	https://drive.google.cor	GoogleMap
015	2025/11/16	36.075227	136.221772	文京一丁目	中1-469	防護柵の破損	https://drive.google.cor	https://drive.google.cor	GoogleMap
016	2025/11/16	36.075124	136.219686	松本四丁目	中1-469	防護柵の破損	https://drive.google.cor	https://drive.google.cor	GoogleMap
017	2025/11/17	36.086116	136.227208	二の宮一丁目	警察	その他	https://drive.google.cor	https://drive.google.cor	GoogleMap
018	2025/11/17	36.085969	136.22734	二の宮一丁目	警察	その他	https://drive.google.cor	https://drive.google.cor	GoogleMap
019	2025/11/17	36.087051	136.228215	二の宮一丁目	警察	その他	https://drive.google.cor	https://drive.google.cor	GoogleMap
020	2025/11/17	36.086957	136.229051	二の宮一丁目	警察	その他	https://drive.google.cor		GoogleMap
021	2025/11/17	36.086936	136.229276	二の宮一丁目	警察	その他	https://drive.google.cor		GoogleMap
022	2025/11/17	36.087699	136.229626	二の宮一丁目	中2-45	ガードレール・車止めポ...	https://drive.google.cor	https://drive.google.cor	GoogleMap
023	2025/11/17	36.092104	136.229732	高木二丁目	北2-170	路面（舗装）のはがれ・...	https://drive.google.cor	https://drive.google.cor	GoogleMap
024	2025/11/17	36.099764	136.226838	舟橋一丁目	県道	その他	https://drive.google.cor	https://drive.google.cor	GoogleMap
025	2025/11/17	36.102601	136.225854	稲多元町	北1-189	その他	https://drive.google.cor	https://drive.google.cor	GoogleMap
026	2025/11/17	36.098263	136.227095	舟橋一丁目	北2-1	防護柵の破損	https://drive.google.cor	https://drive.google.cor	GoogleMap
027	2025/11/17	36.093638	136.228068	高木二丁目	警察	その他	https://drive.google.cor	https://drive.google.cor	GoogleMap
028	2025/11/17	36.093616	136.227903	高木二丁目	警察	その他	https://drive.google.cor	https://drive.google.cor	GoogleMap
029	2025/11/17	36.093675	136.227928	高木二丁目	警察	その他	https://drive.google.cor	https://drive.google.cor	GoogleMap
030	2025/11/17	36.089619	136.228366	二の宮一丁目	県道	ガードレール・車止めポ...	https://drive.google.cor		GoogleMap

想定価格と提供イメージ｜リスクの可視化・共有

含まれる業務

歩行による現地確認
写真・位置・状況の取得
損傷 × 人流 × 周辺条件の記録
定期的な更新
リスク分布
エリア別傾向

含まれないこと

現地追加調査
作業指示の代行
修繕判断の最終責任

価格感（目安）

月額 15万円/月
年額 160万円/年

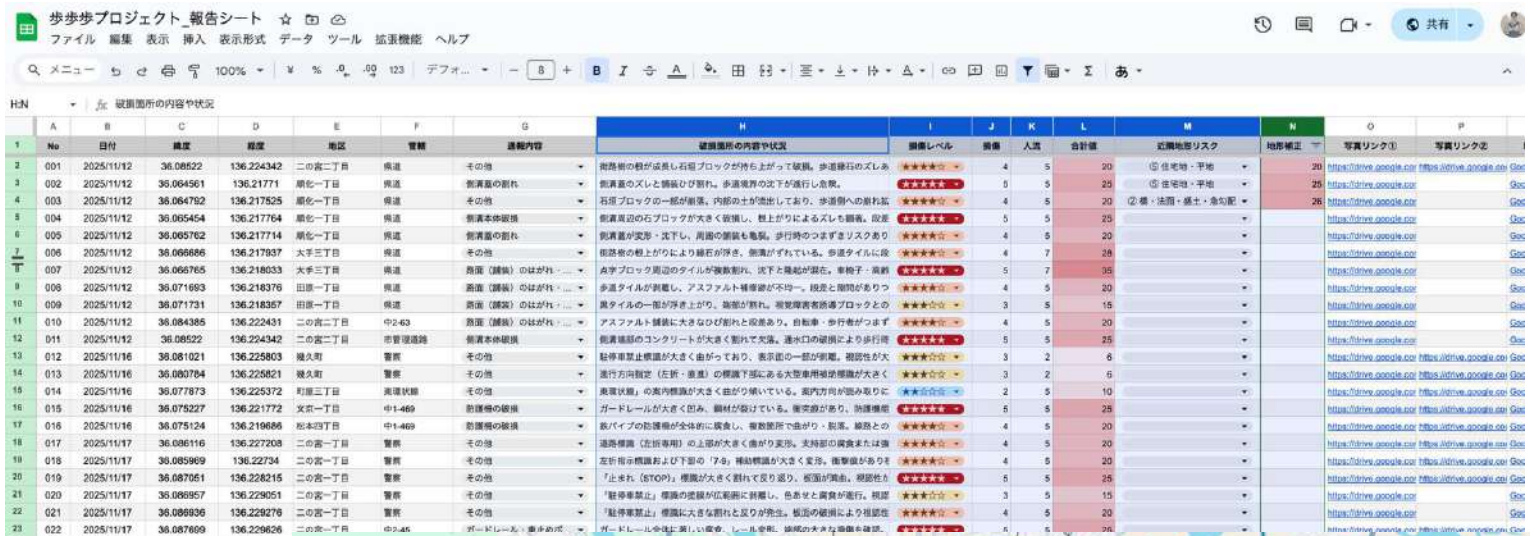

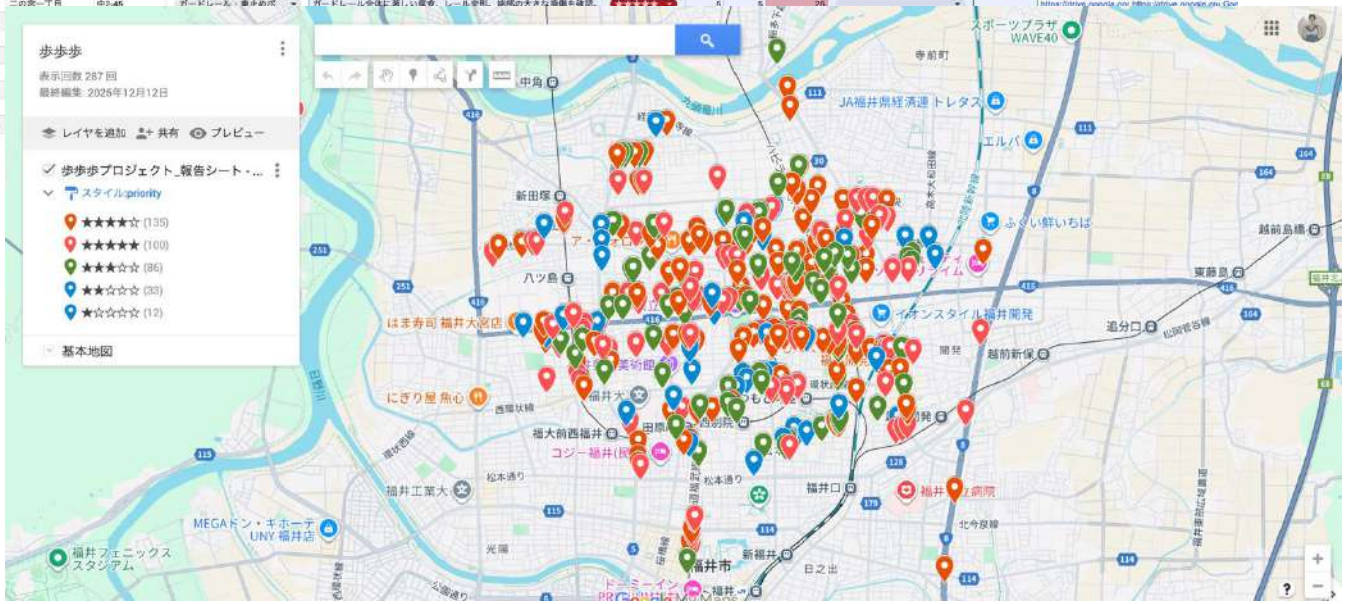

観測対象について（できること／できないこと）

HOHOHOの観測は「歩行によって確認できる範囲」に限定されます。

観測できる主なポイント

・駅前・駅構内周辺（改札外動線含む）
・踏切周辺（歩行者動線側）
・沿線の歩行可能な側道・通学路・生活動線
・駅間で徒歩確認が可能な区間

観測対象外となるポイント

・列車走行中のみ確認可能な区間
・橋梁上・高架上など歩行立ち入り不可エリア
・線路内・保守専用通路

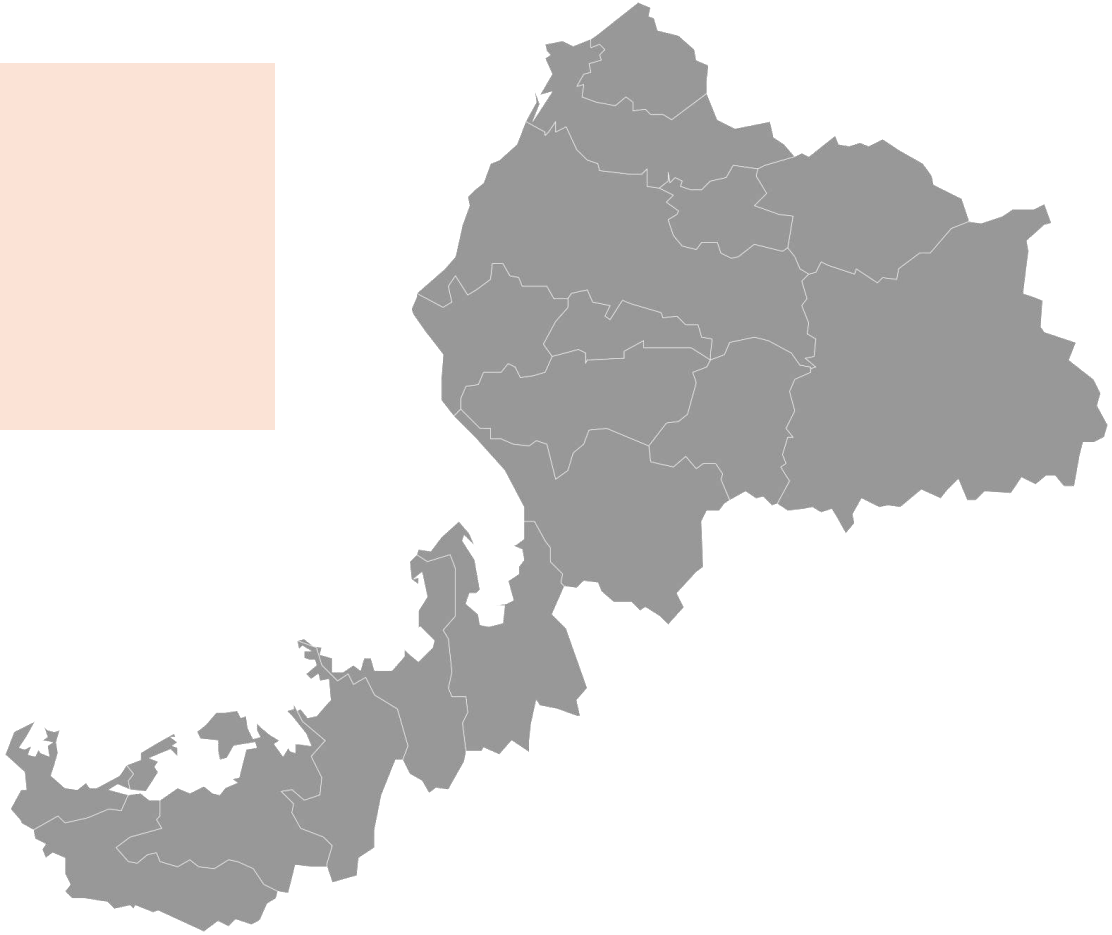

観測体制とスケジュール感

観測体制

観測方法：徒歩のみ　実施人数：1名　1日の実質観測距離：約3km
写真撮影・状況メモ・データ整理含む　対象：歩行で確認できる範囲のみ

観測距離と期間の考え方

・徒歩による観測距離：約3km／日
・記録・整理を含めた現実的なペース
・約1ヶ月で沿線・駅周辺を一巡

初回の1ヶ月で「どこが・どう壊れているか」
という現状把握データを一式揃えることを
目的とします。

2ヶ月目以降

初回一巡後は、
劣化が見られた箇所や
重点的に見たい区間を中心に
部分的・重点的な再観測を行います。

費用の考え方

月額費用：観測・記録・データ整理の対価
交通費：業務遂行に必要な実費を別途精算
※利用区間・頻度は事前に共有

再掲：修繕・点検業務を軽くする「歩行者目線の劣化把握データ」

① 修繕計画に使える「現状把握データ」

駅・踏切・沿線における歩行者動線上の劣化・破損状況の把握、どこがどう壊れているか
どの程度進行しているか「次にどこを直すか」を考える材料

② パトロール頻度を見直すための材料

定期パトロールでは拾いきれない箇所を第三者視点で継続観測。問題が出やすい場所、変化が起きにくい場所「ここは頻度を落としていい」「ここは重点的に見るべき」の判断材料

③ 点検・修繕判断の前工程を外出しできる

社内で毎回やっている「まず現地を見に行く」を減らす
現地確認・写真取得・状況整理。その“最初の一歩”をHOHOHOが担う

今後の展開イメージ

2026年に向けてはスキームの実現を中心に活動予定。2027年以降は活動を市民に広げていく取り組みを行っていく
着地目標：報告用ミニアプリの提供、リージョンペイとの協業。

想定される課題
・市民に対するアプリの認知・利用の壁
・スキーム実現に対する心理的・実務的ハードル

課題に対する方向性
アプリ開発費用が高額になるリスク
→ LINEミニアプリを活用し、最小コストで実装

アプリ認知・利用促進の課題
歩行を活かしたポスティング　動画による活動報告・可視化

リージョンペイ導入の課題
新規導入地域ではなく
すでに導入率の高い地域に「歩歩歩パッケージ」を組み合わせるなど

現時点の位置づけ（理解）
アイデア検証は すでに実地で進んでいる
課題は「需要の有無」ではなく「どう使える形に翻訳するか」

導入実績

※2025年2月末時点

導入実績地域	アプリ累計ダウンロード数	累計決済額	加盟店数
1,132	1,141 万DL	2,143 億円	23.6 万店舗

都道府県での実績は市区町村数で換算